BUKU PANDUAN

Penggunaan Aplikasi **SIPANDA**

Sistem Informasi
Pengelolaan Drainase
Perkotaan

SIPANDA

Kata Pengantar

Alhamdulillah puji syukur kehadirat Allah SWT, kerena atas karuniaNya maka buku petunjuk penggunaan ini telah berhasil diselesaikan.

Buku petunjuk penggunaan ini disusun untuk memberikan informasi bagi pengguna aplikasi Sistem Informasi Pengelolaan Drainase Perkotaan (SiPanda) Dinas Pekerjaan Umum Bidang Sistem Sumber Daya Air.

Semoga buku petunjuk ini dapat memberikan manfaat sesuai dengan tujuan dari ditulisnya buku petunjuk penggunaan ini.

Pontianak, 30 Oktober 2021
Tim Pengembang Aplikasi

Daftar Isi

Kata Pengantar i

Daftar Isi ii

1. Pendahuluan 1

1.1. Tujuan Pembuatan Dokumen 1

1.2 Deskripsi Umum Sistem 1

1. Deskripsi Dokumen 1

2. Sumber Daya yang Dibutuhkan 2

2.1 Perangkat Lunak 2

2.2 Perangkat Keras 2

2.3 Sumber Daya Manusia 2

2.4 Pengenalan dan Pelatihan 2

3. Menu dan Cara Penggunaan 3

Login Aplikasi 3

Lapor Keluhan Drainase 3

Dashboard 4

Saluran per blok 4

Tambah Blok Baru 5

Peta Kawasan Rawan Banjir 6

Aduan Masyarakat 7

Detail Saluran Per Blok 7

Manajemen Akun - Edit Akun 8

Manajemen Data - Elevasi Tanah 9

Manajemen Data - Saluran Per Blok 10

Manajemen Data - Saluran terkoneksi 10

Akun 11

1. Pendahuluan

1.1. Tujuan Pembuatan Dokumen

Dokumen petunjuk penggunaan ini dibuat untuk tujuan sebagai berikut:

1. Menggambarkan dan menjelaskan penggunaan aplikasi untuk superadmin, admin, pengguna biasa dan tamu.

2. Sebagai panduan instalasi, konfigurasi dan penggunaan aplikasi ini

1.2 Deskripsi Umum Sistem

1. Deskripsi Umum Aplikasi

Pengembangan aplikasi ini adalah untuk mempermudah Dinas PUPR mengelola data terkait saluran drainase yang ada di kabupaten kubu raya.

2. Deskripsi Umum Kebutuhan Aplikasi Yang Akan Diimplementasikan

Deskripsi umum kebutuhan aplikasi yang akan diimplementasikan meliputi semua informasi yang bersifat teknis yang menjadi acuan dalam pengembangan aplikasi.

1. Deskripsi Dokumen

Dokumen ini dibuat untuk memberikan panduan penggunaan aplikasi SiPanda. Dokumen ini berisikan informasi sebagai berikut:

Dokumen ini dibuat untuk memberikan panduan penggunaan aplikasi Sistem Informasi pengelolaan drainase perkotaan (SiPanda) Dinas Pekerjaan Umum Bidang Sumber Daya Air. Dokumen ini berisikan informasi sebagai berikut:

1. BAB 1
   Berisi informasi umum yang merupakan bagian pendahuluan, yang meliputi tujuan pembuatan dokumen, deskripsi umum sistem serta deskripsi dokumen.
2. BAB 2
   Berisi perangkat yang dibutuhkan untuk penggunaan aplikasi SiPanda Dinas Pekerjaan Umum Bidang Sumber Daya Air meliputi perangkat lunak dan perangkat keras.
3. BAB 3
   Berisi petunjuk penggunaan aplikasi Sistem Informasi Pengelolaan Drainase Perkotaan (SiPanda) Dinas Pekerjaan Umum Bidang Sumber Daya Air yang diperuntukkan untuk Dinas Pekerjaan Umum khususnya Bidang Sumber Daya Air beserta instansi terkait yang memerlukan data terkait saluran drainase di Kabupaten Kubu Raya.

2. Sumber Daya yang Dibutuhkan

2.1 Perangkat Lunak

Perangkat lunak yang digunakan dalam pengujian adalah aplikasi browser seperti Mozila Firefox, Google Chrome atau aplikasi browser lainnya.

2.2 Perangkat Keras

Perangkat keras yang dilibatkan dalam pengujian aplikasi ini terbagi menjadi versi android dan versi web. Untuk versi android perangkat kers yang dibutuhkan hanya ponsel pintar berbasis android sedangkan perangkat keras yang dibutuhkan untuk menggunakan aplikasi versi website adalah sebagai berikut:

1. Android yang memiliki koneksi jaringan internet
2. Komputer atau Laptop yang memiliki koneksi jaringan internet.
3. Mouse sebagai peralatan antarmuka
4. Monitor sebagai peralatan antarmuka
5. Keyboard sebagai peralatan antarmuka.

2.3 Sumber Daya Manusia

Sumber daya manusia yang akan menggunaan aplikasi ini dibagi menjadi suparadmin, admin, pengguna biasa dan tamu. Masing masing klasifikasi pengguna adala sebagai berikut:

1. Superadmin, merupakan kepala bidang Sumber Daya Air dari Dinas Pekerjaan Umum Kabupaten kubu raya dan tim pengembang.
2. Admin, merupakan staf bidang Sumber Daya Air dari Dinas Pekerjaan Umum Kabupaten Kubu Raya
3. Pengguna biasa, merupakan pengguna dari instansi terkait yang membutuhkan data terkait saluran drainase Kabupaten Kubu Raya.
4. Tamu, merupakan masyarakat umum yang membutuhkan informasi mengenai saluran drainase kabupaten Kubu Raya.

2.4 Pengenalan dan Pelatihan

Sumber daya manusia yang terlibat dalam operasinal penggunaan aplikasi ini sehari-hari akan diberikan pengenalan yang cukup untuk menggunakan aplikasi SiPanda.

3. Menu dan Cara Penggunaan

Login Aplikasi

Untuk menggunakan aplikasi pengguna perlu melakukan login terlebih dahulu menggunakan akun yang diberikan oleh superadmin atau login sebagai tamu dengan akses terbatas. Tampilan halaman login dapat dilihat pada gambar 3.1.

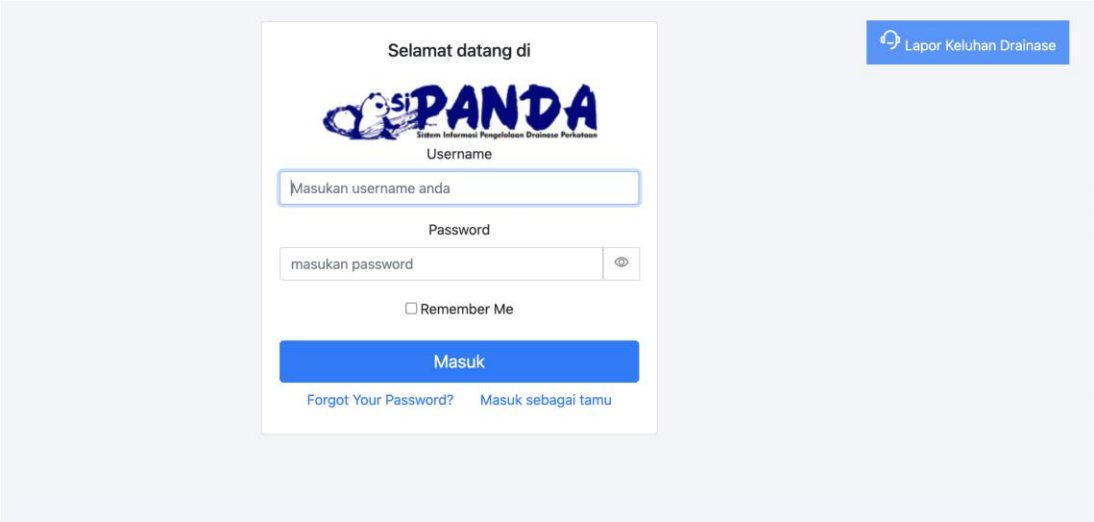

Gambar 3.1 Halaman Login

Langkah Langkah

1. Pengguna menginputkan email dan password atau klik “masuk sebagai tamu”.
2. Pengguna mencentang **“Remember me”** berfungsi untuk memudahkan login kembali di kemudian hari (OPSIONAL)
3. Klik masuk

Lapor Keluhan Drainase

Untuk melaporkan masalah terkait saluran drainase, pengguna dapat memberikan masukan kepada Dinas Pekerjaan Umum Bidang Sumber Daya Air melalui aplikasi SiPanda. Pengguna cukup melakukan klik pada tombol lapor keluhan drainase lalu mengisi form yang diberikan. Tampilan lapor keluhan drainase dapat dilihat pada gambar 3.2.

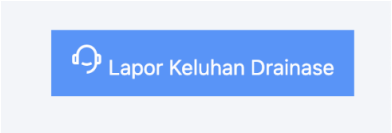

Gambar 3.2 Menu Lapor Keluhan Drainase

1. Klik “Lapor keluhan drainase” pada halaman awal

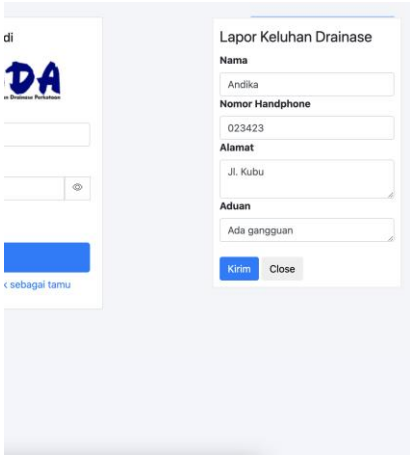

2. Masukkan detail keluhan kemudian lalu klik kirim.

Dashboard

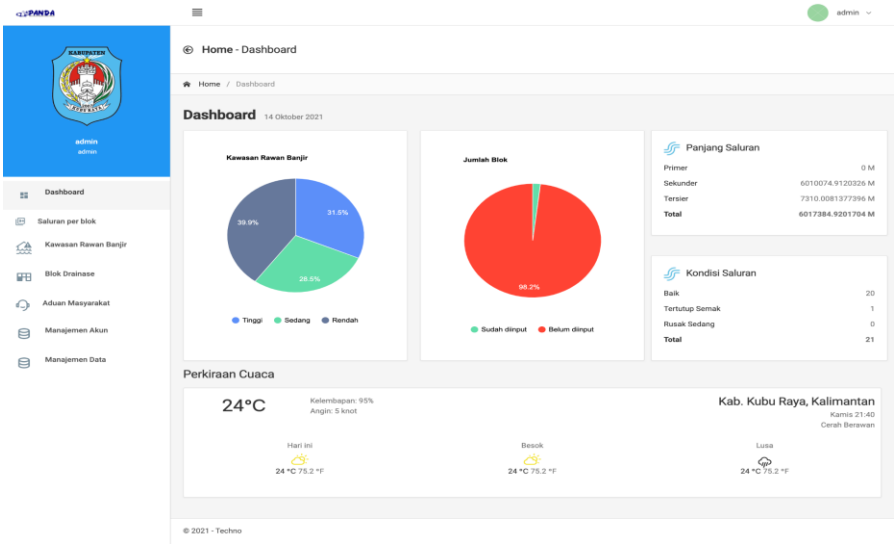

Gambar 3.4 Halaman Dashboard

Dashboard berfungsi untuk melihat semua menu utama secara keseluruhan dan menampilkan data-data yang secara umum. Tampilan antar muka dashboard dapat dilihat pada gambar 3.4.

Saluran per blok

Saluran per blok memungkinkan admin dan super admin untuk mengelola data blok-blok saluran yang ada di kabupaten kubu raya serta menampilkan data blok saluran secara lengkap. Pengguna dapat mencari blok berdasarkan nama lokasi, kode blok, kecamatan, luas dan waktu pembuatan data blom tersebut. Pengguna juga dapat menghapus

data, menambahkan blok, menghapus dan membagikan data blok saluran kepada user lain melalui whatsapp. Tampilan antar muka saluran per blok dapat dilihat pada gambar 3.5.

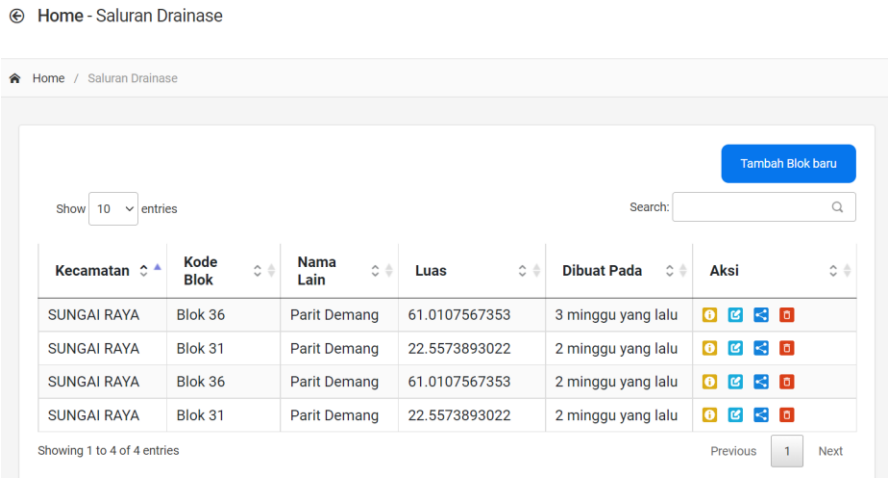

Gambar 3.5 Menu Saluran Per Blok

1. Jika ingin menambah blok baru, klik Tambah Blok Baru.
2. Jika ingin mengurutkan hasil pencarian, klik tombol scroll untuk turun maupun naik
3. Jika ingin mencari suatu kata kunci, ketikkan di kolom search.
4. Jika ingin melihat detail blok yang sudah ada, klik ikon berwarna kuning
5. Jika ingin mengedit detail saluran drainase yang sudah ada, klik ikon tulis berwarna biru muda
6. Jika ingin membagikan link peta ke Whatsapp, klik ikon share berwarna biru tua
7. Jika ingin menghapus data, klik ikon sampah berwarna merah

Tambah Blok Baru

Admin dan superadmin dapat menambahkan blok saluran. Pada bagian ini pengguna mengisi form dan mengunggah data RAB dan peta (dalam format .geojson) untuk menambahkan blok baru. Tampilan antarmuka form tambah blok dapat dilihat pada gambar 3.6.

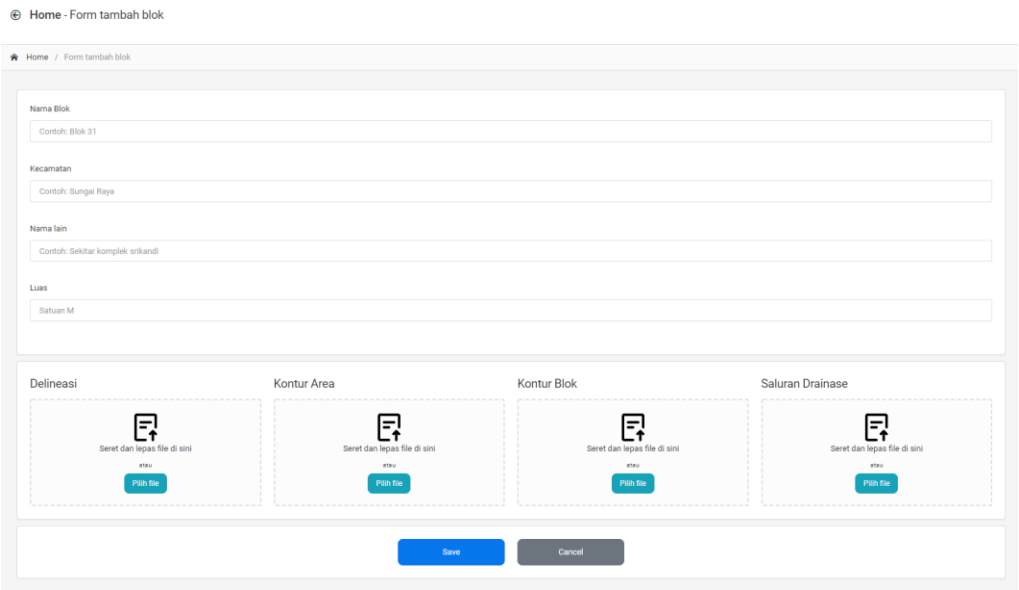

Gambar 3.6 Tambah Blok Baru

Peta Kawasan Rawan Banjir

Pengguna dapat melihat peta kerawanan banjir yang menggambarkan tingkat kerawanan banjir berupa peta. Tingkat kerawanan banjir dinilai berdasarkan skor banjir yang didapat dari survei langsung ke lapangan. Tampilan antarmuka peta kawasan rawan banjir dapat dilihat pada gambar 3.7.

Gambar 3.7 Peta Kawasan Rawan Banjir

1. Panduan tinggi risiko dapat dilihat di kolom putih kiri atas
2. Jika ingin melihat peta dengan halaman penuh, klik tombol kotak putih kanan atas

3. Klik tombol plus untuk melihat lebih dekat (zoom in) dan tombol minus untuk melihat lebih jauh (zoom out)

Aduan Masyarakat

Admin dan superadmin dapat melihat maupun menanggapi aduan yang diberikan oleh masyarakat. Admin dan superadmin dapat membalas aduan melalui email yang diberikan oleh pengguna saat mengisi form. Tampilan antarmuka fitur aduan masyarakat dapat dilihat pada gambar 3.8.

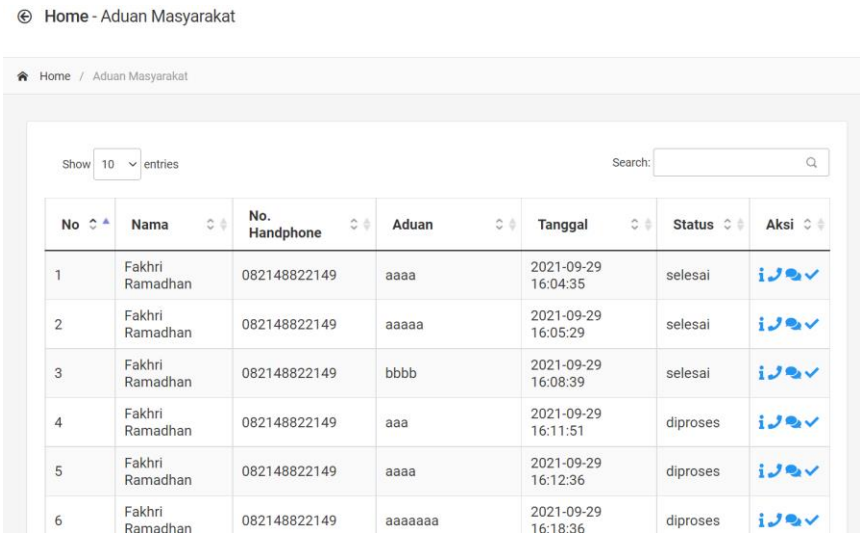

Gambar 3.8 Aduan Masyarakat

Detail Saluran Per Blok

Pada bagian ini pengguna dapat melihat data blok drainase secara lengkap. Data blok drainase disajikan dalam bentuk peta interaktif yang dapat di klik secara langsung.Pengguna dapat memilih jenis peta yang ingin ditampilkan dengan menekan tombol di sebelah kiri peta. Pengguna juga dapat melihat RAB yang telah di upload sebelumnya. Tampilan antarmuka detail saluran per blok dapat dilihat pada gambar 3.9.

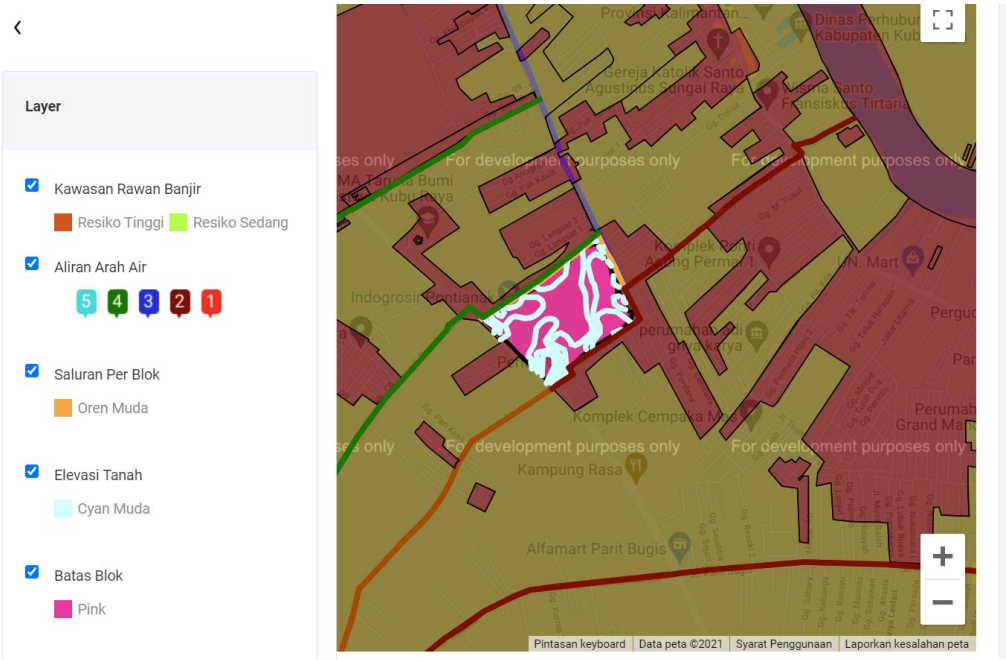

Gambar 3.9 Detail Saluran Per Blok

Klik tanda centang untuk melihat lapisan peta

Manajemen Akun - Edit Akun

Superadmin dapat mengelola akun pengguna melalui menu manajemen akun. Pengguna dapat menambah, mengedit, melihat maupun menghapus data pengguna melalui manajemen akun. Tampilan antarmuka edit akun dapat dilihat pada gambar 3.10. Pengguna cukup mengisi form yang disediakan untuk menedit dan menambahkan pengguna lain. Untuk menghapus penguna lain, superadmin dapat meneka tombol hapus yang ada pada manajemen akun.

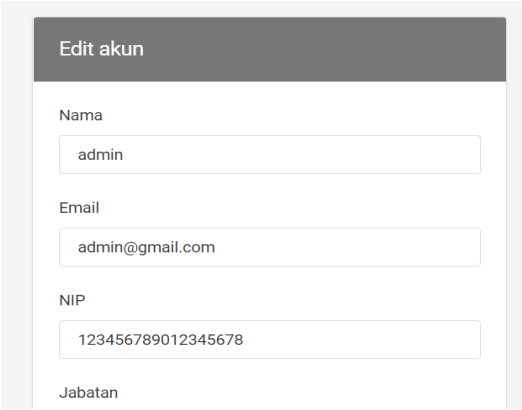

Gambar 3.10 Manajemen Akun - Edit Akun

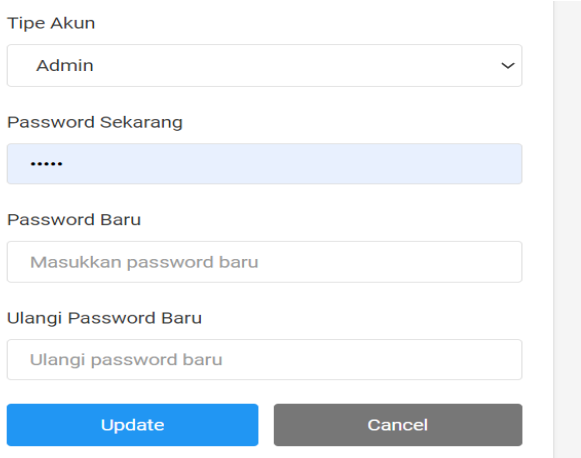

Gambar 3.11 Manajemen Akun - Edit Akun

Manajemen Data - Elevasi Tanah

Digunakan untuk melihat dan mengedit data elevasi tanah. Pengguna dapat mencari berdasarkan FID, nama blok, kecamatan maupun elevasi dengan menuliskan kata kunci pada input search seperti pada gambar 3.12. Untuk mengedit data tersebut, pengguna cukup menekan tombol edit pada kolom aksi seperti pada gambar 3.12. Lalu akan muncul isian yang berkaitan dengan elevasi tanah.

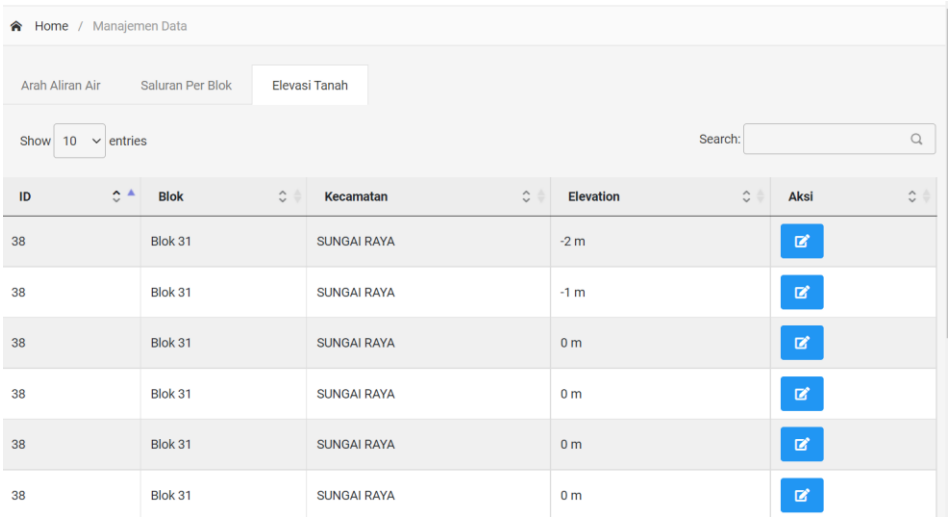

Gambar 3.12 Manajemen Data - Elevasi Tanah

Tombol aksi jika ingin mengedit data elevasi tanah

Manajemen Data - Saluran Per Blok

Digunakan untuk melihat dan mengatur data saluran drainase dari semua blok. Pengguna dapat melihat semua data saluran drainase dan mencari berdasarkan nama blok, nama saluran, kondisi dan kewenangan. Superadmin dapat mengedit data saluran dengan klik tombol edit yang telah disediakan seperti pada gambar 3.13 lalu mengisi form yang sudah disediakan.

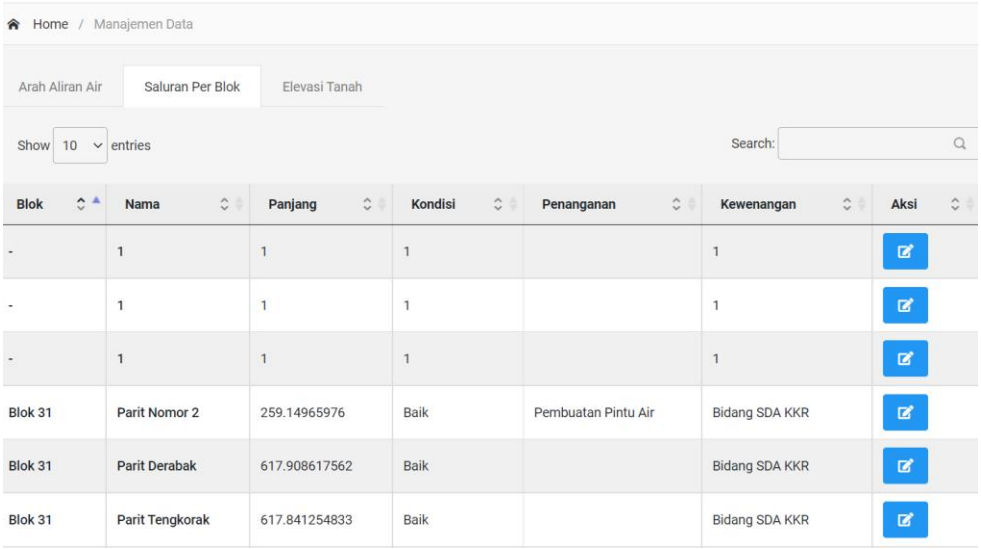

Gambar 3.13 Manajemen Data - Saluran Per Blok

Tombol aksi jika ingin mengedit data saluran per blok

Manajemen Data - Saluran terkoneksi

Bagian ini dapat digunakan admin maupun superadmin untuk melihat dan mengatur data saluran terkoneksi. Tampilan antarmuka manajemen data saluran terkoneksi dapat dilihat pada gambar 3.14.

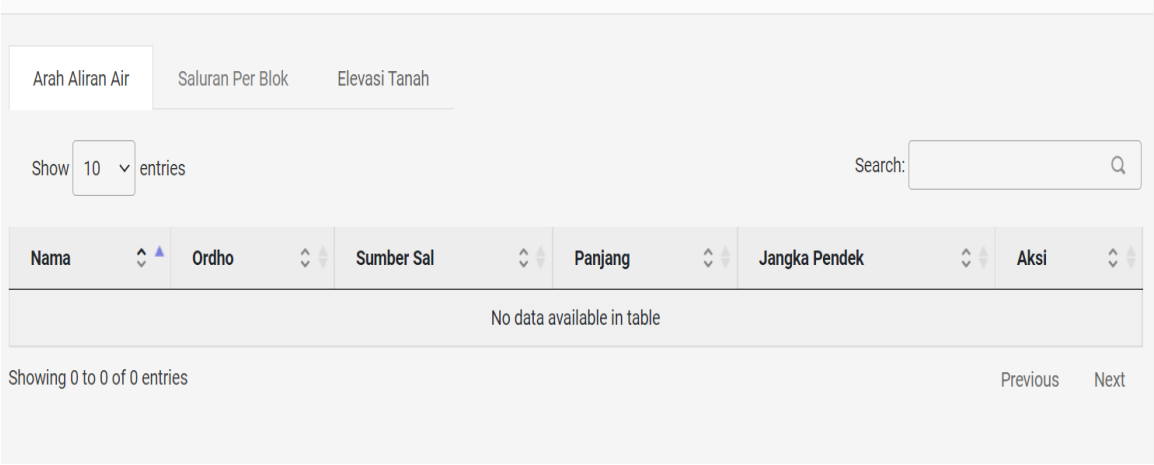

Gambar 3.14 Manajemen Data - Arah Aliran Air

Akun

Pada bagian ini pengguna dapat mengatur data identitas maupun password pengguna. Untuk melakukan perubahan data identitas, pengguna cukup menginputkan data yang diinginkan pada form seperti pada gambar 3.15. Untuk mengakses halaman ini pengguna cukup klik foto profil di bagian kanan atas lalu memilih menu *my profile*. .

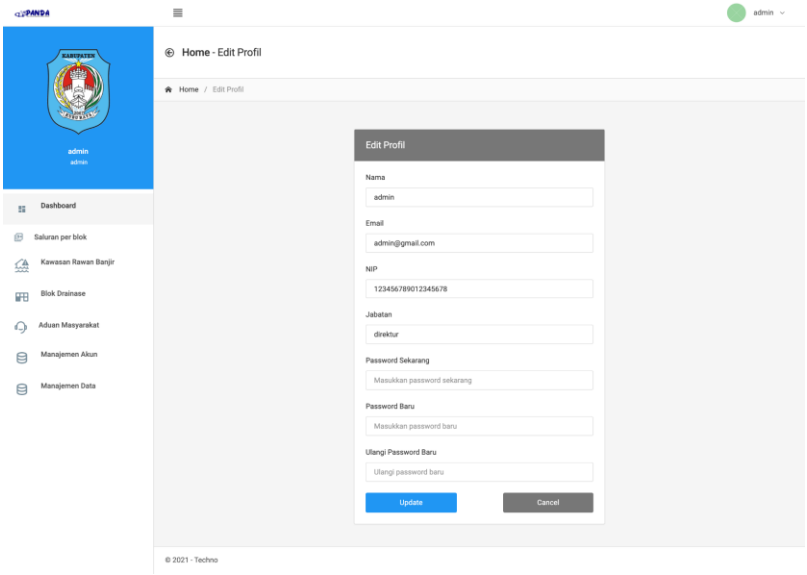
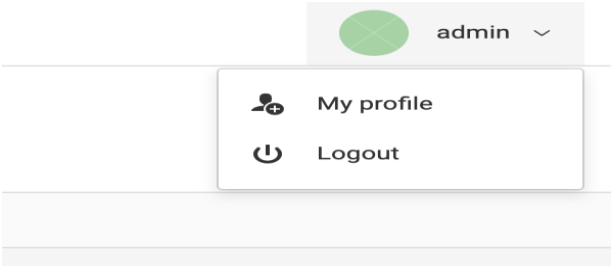
Gambar 3.15 Akun